FALCON-PAD

User Guide — English

Real-time tactical map for Falcon BMS 4.38

v0.2 by Riesu

1. Getting Started

Launch Falcon-PAD.exe and open your browser. The application starts a local web server — no installation needed.

Step	Action
1	Launch Falcon-PAD.exe
2	Open http://localhost:8000 in Chrome or Edge
3	On tablet: open http://YOUR_PC_IP:8000
4	Start BMS, load a mission, fly

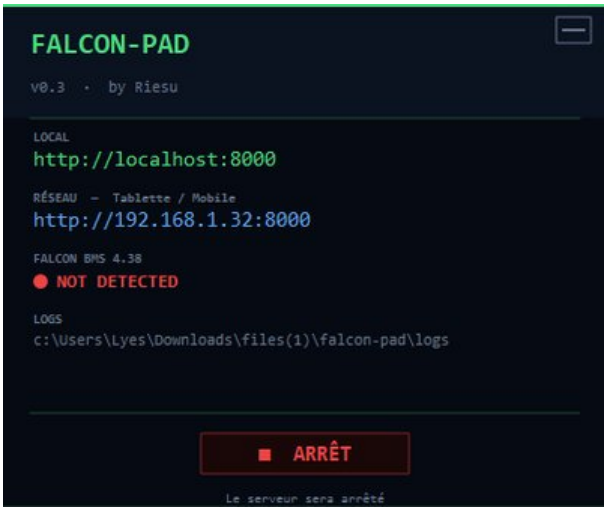

The Falcon-PAD desktop window — shows server status, URLs, and BMS connection

First Time Setup

Windows Firewall — run this command once to allow tablet access:

```
netsh advfirewall firewall add rule name="Falcon-PAD" dir=in action=allow protocol=TCP
localport=8000
```

BMS Configuration — add these lines to Falcon BMS User.cfg:

```
set g_bTacviewRealTime 1
set g_bTacviewRealTimeHost 1
```

2. The Tactical Map

The map shows your aircraft position, heading, altitude and speed in real-time. Steerpoints, flight plan route, PPT threat circles, airports, and datalink contacts are all displayed.

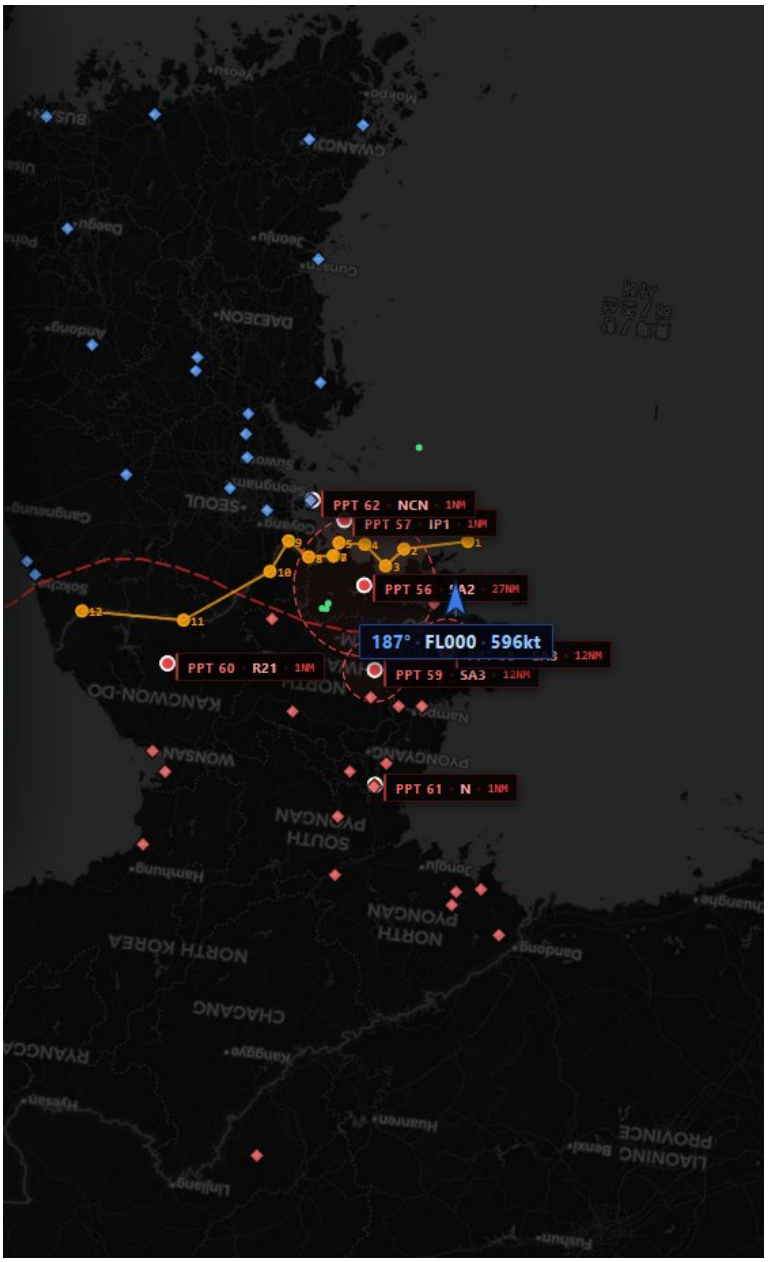

Live tactical map — steerpoints (amber), PPT threat circles (red), flight plan (red dashed), aircraft (blue), airports (blue diamonds)

Status bar — BMS connection, callsign, clock, and settings

Toolbar

Button	Function
Import	Upload a .ini mission file manually
Note	Create a sticky note on the map
Ruler	Measure distance between two points (NM)
Arrow	Draw a direction arrow with distance label
Clear	Remove all drawings from the map
Color	Pick the drawing color
Compass	Toggle North Up / Track Up
Follow	Auto-center map on your aircraft
Layers	Switch map tiles, toggle airports/runways/PPT

Compass — North Up / Track Up

North Up (green) — default mode. The map is fixed with north at the top. Your aircraft icon rotates on the map following its heading.

Track Up (red) — the map rotates so your aircraft always points up, like a real GPS navigation display.

> 💡 *Dragging the map manually switches back to North Up automatically.*

3. Mission Auto-Loading

Falcon-PAD watches your BMS User\Config folder for .ini files containing mission data. When BMS saves your DTC (callsign.ini), the app detects it and refreshes the map.

How it works

1. Load a Tactical Engagement or Campaign mission in BMS
2. Modify your DTC (radios, steerpoints, targets...)
3. BMS saves your callsign.ini (e.g. Riesu.ini) to User\Config
4. Falcon-PAD detects the change within 3 seconds
5. Steerpoints, flight plan and PPT circles appear on the map
6. The tablet receives the same update automatically

> 💡 *You can also import a .ini file manually using the upload button in the toolbar.*

4. Kneeboard

The Kneeboard tab provides everything you need in the cockpit.

Kneeboard — checklist sections in accordion view

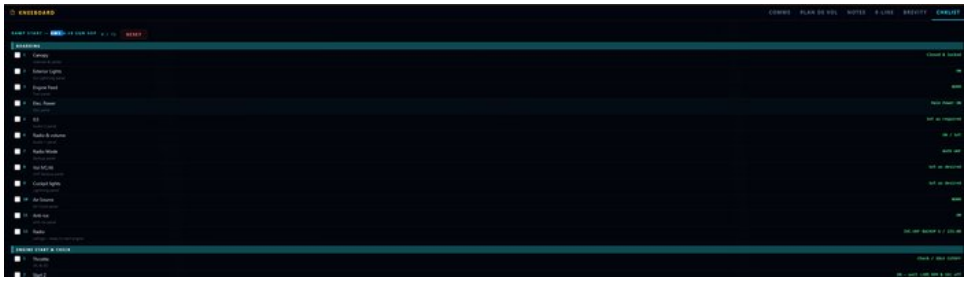

Expanded checklist — items with checkboxes, status, and location

Tabs

Tab	Content
CHKLIST	Interactive ramp start checklist with checkbox items and progress counter
COMMS	Korean theater frequency table (GUARD, AWACS, tankers, towers)
FLIGHT PLAN	Editable flight plan fields and mission notes
NOTES	Free-form sticky notes
9-LINE	Standard 9-LINE CAS brief form with COPY to clipboard
BREVITY	28 NATO/BMS brevity codes with definitions

Checklist

The RAMP START checklist is organized in collapsible accordion sections: Boarding, Engine Start, Avionics, Settings, Before Taxi, Before Take Off. Click a section to expand it. Each item has a checkbox — progress is saved between reloads. The RESET button clears all checks.

5. Tablet Setup

Falcon-PAD is designed to run on a tablet placed next to your flight sim as a kneeboard. The PC runs the server and BMS, the tablet connects via WiFi.

Connection

1. PC and tablet must be on the same WiFi network
2. Open the URL shown in the Falcon-PAD window (e.g. http://192.168.1.32:8000)
3. Bookmark the URL — no login required
4. Mission data syncs automatically every 3 seconds

Touch Controls

Gesture	Action
One finger drag	Pan the map
Pinch	Zoom in/out
Drag note header	Move a sticky note
Tap + tap	Set ruler/arrow start and end points

6. Briefing Viewer

Upload and view mission briefing documents directly in the app.

Feature	Details
Supported formats	PDF, PNG, JPEG, DOCX
PDF rendering	Page by page with navigation controls
Max file size	50 MB
File management	Delete files from the built-in list

7. File Structure

```
Falcon-PAD/
  Falcon-PAD.exe
  assets/
    logo_app.png       (app icon)
    logo_moyen.png     (banner)
  logs/                (auto-created)
  briefing/            (your documents)
  config/              (saved settings)
```

FALCON-PAD

Guide utilisateur — Français

Carte tactique temps réel pour Falcon BMS 4.38

1. Démarrage

Lancez Falcon-PAD.exe et ouvrez votre navigateur. L'application démarre un serveur web local — aucune installation nécessaire.

Étape	Action
1	Lancer Falcon-PAD.exe
2	Ouvrir http://localhost:8000 dans Chrome ou Edge
3	Sur la tablette : ouvrir http://IP_DU_PC:8000
4	Lancer BMS, charger une mission, voler

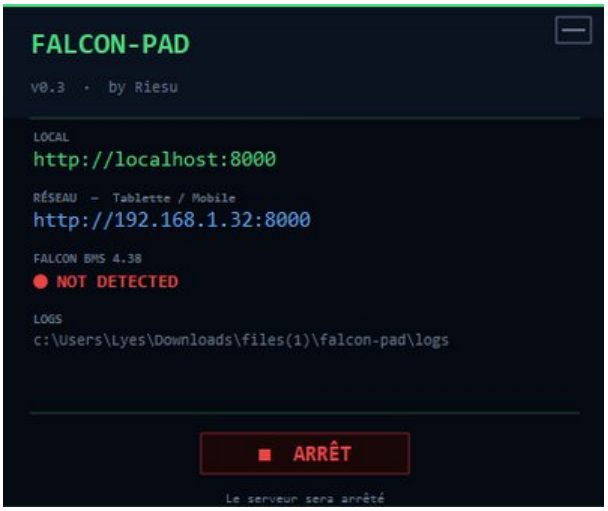

Fenêtre Falcon-PAD — statut serveur, URLs et connexion BMS

Premier lancement

Pare-feu Windows — exécuter cette commande une seule fois :

```
netsh advfirewall firewall add rule name="Falcon-PAD" dir=in action=allow protocol=TCP
localport=8000
```

Configuration BMS — ajouter dans Falcon BMS User.cfg :

```
set g_bTacviewRealTime 1
set g_bTacviewRealTimeHost 1
```

2. La carte tactique

La carte affiche la position, le cap, l'altitude et la vitesse de votre avion en temps réel. Les steerpoints, le plan de vol, les cercles de menace PPT, les aéroports et les contacts datalink sont tous affichés.

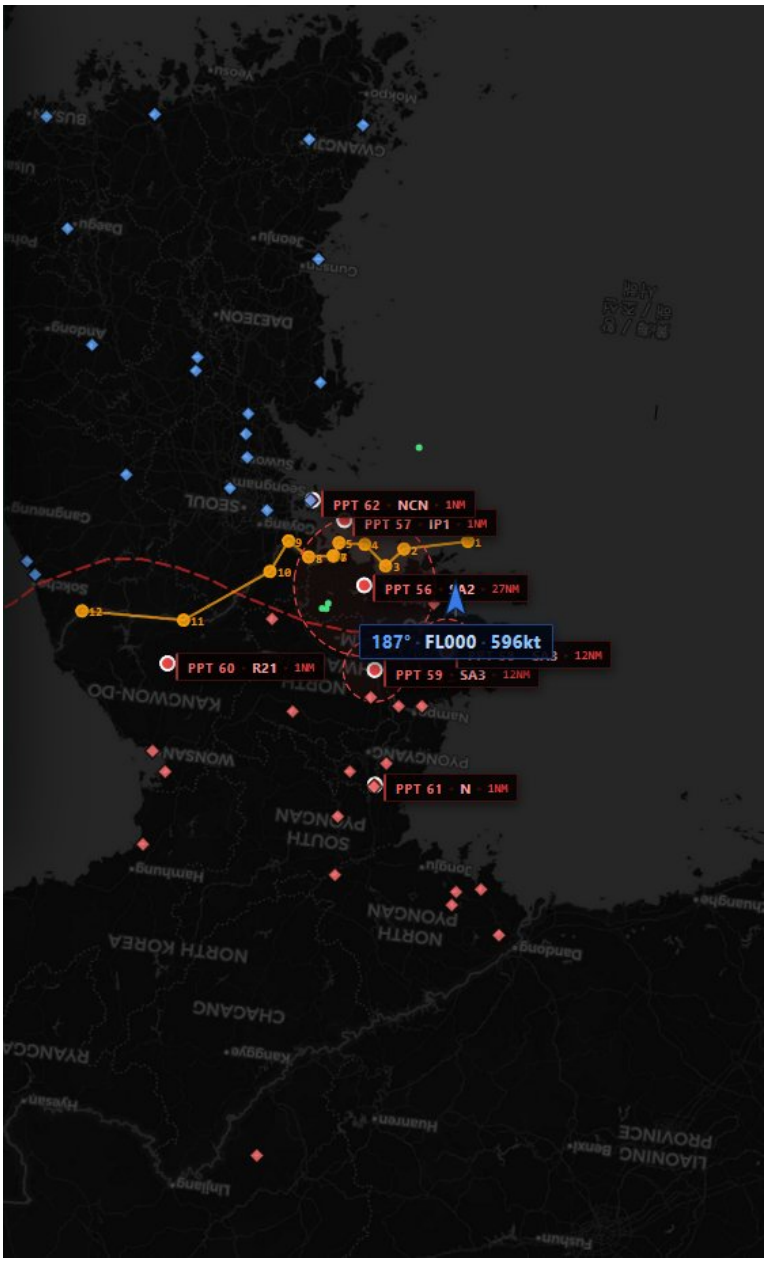

Carte tactique — steerpoints (ambre), cercles PPT (rouge), plan de vol (rouge pointillé), avion (bleu), aéroports (losanges bleus)

Barre d'outils

Bouton	Fonction
Import	Charger un fichier .ini de mission manuellement
Note	Créer une note autocollante sur la carte
Règle	Mesurer la distance entre deux points (NM)
Flèche	Tracer une flèche directionnelle avec distance
Effacer	Supprimer tous les tracés de la carte
Couleur	Choisir la couleur de tracé
Boussole	Basculer Nord en haut / Track Up
Suivi	Centrage automatique sur l'avion
Couches	Changer les tuiles, afficher aéroports/pistes/PPT

Boussole — Nord en haut / Track Up

Nord en haut (vert) — mode par défaut. La carte est fixe avec le nord en haut. L'avion tourne sur la carte selon son cap.

Track Up (rouge) — la carte tourne pour que votre avion pointe toujours vers le haut, comme un GPS de navigation.

> 💡 *Glisser la carte manuellement revient automatiquement en Nord en haut.*

3. Chargement automatique de mission

Falcon-PAD surveille le dossier User\Config de BMS pour les fichiers .ini contenant les données de mission. Quand BMS sauvegarde votre DTC (callsign.ini), l'application détecte le changement et rafraîchit la carte.

Comment ça marche

1. Charger une TE ou mission Campaign dans BMS
2. Modifier la DTC (radios, steerpoints, cibles...)
3. BMS sauvegarde votre callsign.ini (ex: Riesu.ini) dans User\Config
4. Falcon-PAD détecte le changement en 3 secondes
5. Steerpoints, plan de vol et cercles PPT apparaissent sur la carte
6. La tablette reçoit la même mise à jour automatiquement

> 💡 *Vous pouvez aussi importer un .ini manuellement via le bouton upload de la barre d'outils.*

4. Kneeboard

L'onglet Kneeboard donne accès à tout le nécessaire en cockpit.

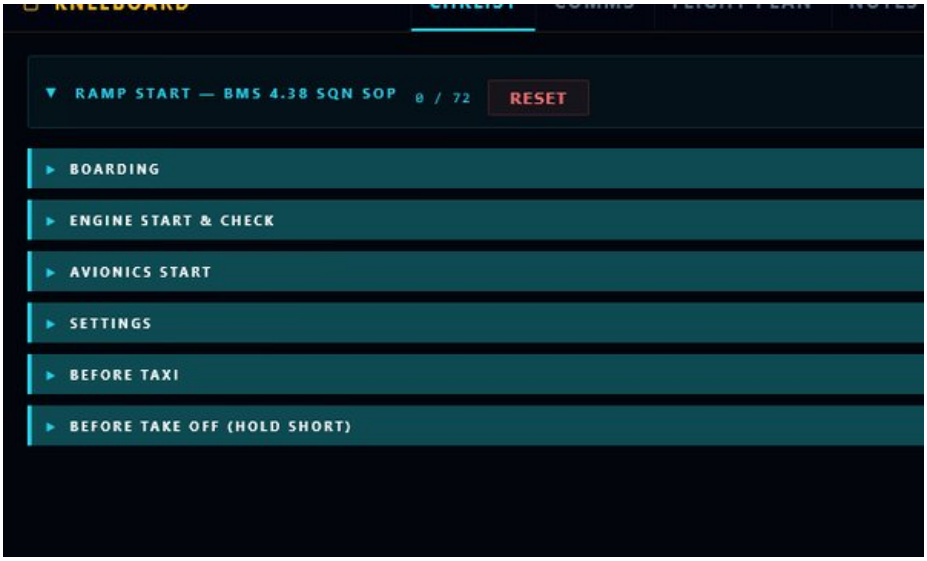

Kneeboard — sections de checklist en accordéon

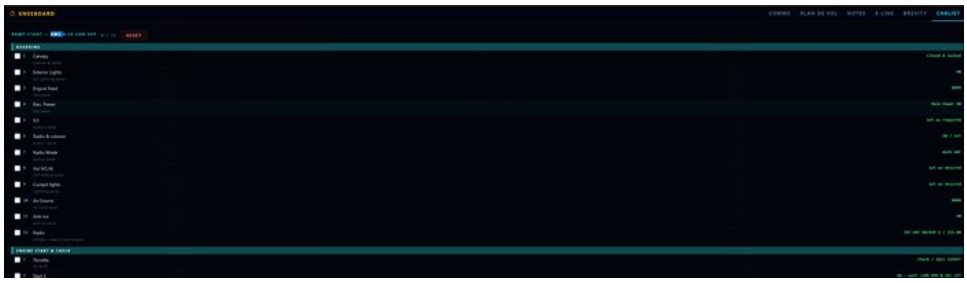

Checklist dépliée — items avec cases à cocher, statut et emplacement

Onglet	Contenu
CHKLIST	Checklist ramp start interactive avec cases à cocher et compteur de progression
COMMS	Table de fréquences du théâtre coréen (GUARD, AWACS, ravitaillement, tours)
FLIGHT PLAN	Champs plan de vol éditables et notes de mission
NOTES	Notes libres
9-LINE	Formulaire 9-LINE CAS standard avec COPY dans le presse-papier
BREVITY	28 codes brevity NATO/BMS avec définitions

5. Configuration tablette

Falcon-PAD est conçu pour être utilisé sur une tablette posée à côté du simulateur, comme un kneeboard. Le PC fait tourner le serveur et BMS, la tablette se connecte en WiFi.

Connexion

1. Le PC et la tablette doivent être sur le même réseau WiFi
2. Ouvrir l'URL affichée dans la fenêtre Falcon-PAD (ex: http://192.168.1.32:8000)
3. Ajouter l'URL en favori — pas de login nécessaire
4. Les données mission se synchronisent toutes les 3 secondes

Contrôles tactiles

Geste	Action
Glisser un doigt	Déplacer la carte
Pincer	Zoomer / dézoomer
Glisser l'en-tête note	Déplacer une note
Toucher + toucher	Placer début et fin de règle/flèche

6. Visionneuse de briefing

Uploadez et consultez vos documents de briefing directement dans l'application.

Fonctionnalité	Détails
Formats supportés	PDF, PNG, JPEG, DOCX
Rendu PDF	Page par page avec contrôles de navigation
Taille max	50 Mo
Gestion fichiers	Suppression depuis la liste intégrée

7. Structure des fichiers

```
Falcon-PAD/
  Falcon-PAD.exe
  assets/
    logo_app.png       (icône application)
    logo_moyen.png     (bannière)
  logs/                (créé automatiquement)
  briefing/            (vos documents)
  config/              (paramètres sauvegardés)
```